Id:0CC5649A20AD997B

PREFEITURA MUNICIPAL DE
Anísio de Abreu
UMA CIDADE DE TODOS!

ESTADO DO PIAUÍ
PREFEITURA MUNICIPAL DE ANÍSIO DE ABREU
Rua Maria da Mercês Ribeiro, nº 406, Centro
CNPJ: 06.553.630/0001-70 / CEP. 64.780-000
E-MAIL: pmanisiodeabreupi@gmail.com

EXTRATO DE CONTRATO

CONTRATO: 184/2025**; PROCESSO Nº**: 001.0004732/2025**; ADESÃO/CARONA Nº:** 002/2025**; CONTRATANTE:** PREFEITURA MUNICIPAL DE ANÍSIO DE ABREU - PI. **CONTRATADO:** PRIME EMPREENDIMENTOS LTDA, CNPJ 42.958.375/0001-09. **OBJETO:** ADESÃO AO SRP DO MUNICÍPIO DE BARRA D'ALCÂNTARA - PI, NA CONDIÇÃO DE CARONA, ATA DE REGISTRO DE PREÇOS Nº 005/2025, QUE TEM COMO OBJETO REGISTRO DE PREÇOS, A EVENTUAL E FUTURA AQUISIÇÃO, DE FORMA PARCELADA, DE VEÍCULOS AUTOMOTORES ZERO QUILÔMETRO, DESTINADOS A ATENDER ÀS NECESSIDADES DA ADMINISTRAÇÃO MUNICIPAL – REFERENTE AO PREGÃO ELETRÔNICO SRP Nº 023/2025. (PUBLICAÇÃO TERESINA - PI, QUARTA – FEIRA * 03 DE DEZEMBRO DE 2025 * DIÁRIO OFICIAL DAS PREFEITURAS PIAUIENSES, EDIÇÃO Nº MCXVII). **VALOR:** R$ 365.000,00 (trezentos sessenta cinco mil e quinhentos reais). **FONTE DE RECURSO:** FPM / FMS / ICMS / RECURSOS PROPRIOS / EMENDA ESPECIAL. **ASSINATURA DO CONTRATO:** 19 DE DEZEMBRO DE 2025. **VIGÊNCIA:** 19 DE DEZEMBRO DE 2025 A 18 DE DEZEMBRO DE 2026. Anísio de Abreu – PI, 19 de dezembro de 2025. Joelma Maria Soares Macedo Oliveira. Secretaria Municipal de Saúde.

Id:12527A7B96D59A11

PREFEITURA MUNICIPAL DE
AVELINO LOPES
COMPROMISSO COM O POVO!

DECLARAÇÃO DE DOMÍNIO PÚBLICO

O município de **AVELINO LOPES**, estado do Piauí, pessoa jurídica de direito público, inscrito no CNPJ sob o **Nº 06.554.281/0001-00**, com sede na **Praça Mercado, S/N, Centro, CEP: 64.965-000, na sede do Município de AVELINO LOPES – PI**, representado pelo Prefeito Municipal **FLÁVIO JOSÉ ALVES**. Declara instituir os autos do presente instrumento tem como objetivo o estabelecimento da mútua cooperação entre os participantes, com vistas a execução das obras e serviços de **PERFURAÇÃO DE POÇOS E IMPLANTAÇÃO DE SISTEMAS SIMPLIFICADOS DE ABASTECIMENTO DE ÁGUA EM LOCALIDADES DA ZONA RURAL DO MUNICÍPIO DE AVELINO LOPES NO ESTADO DO PIAUÍ**, as quais são de domínio Público do Município, e por ser bens de uso comum do povo, com disposto no art 98 e 99 do Código Civil vigente, independe de registro em cartório de registro de imóveis e hipotecas.

LOCALIDADE	LATITUDE	LONGITUDE
PAJEÚ	10°01'21.47"S	44° 6'25.15"W
PALESTINA	10°03'44.16"S	44° 4'16.57"W
LAGOINHA	10°07'36.65"S	43°58'59.55"W
DIONIZINHO	10°18'02.13"S	43°59'18.78"W
POÇO DO GIRAU	10°07'49.63"S	43°50'42.42"W
LAGOA NOVA	10°03'38.03"S	43°52'20.97"W

Avelino Lopes - PI, em 27 de novembro de 2025

FLAVIO JOSE ALVES:47363088349
Assinado de forma digital por FLAVIO JOSE ALVES:47363088349
Dados: 2025.12.20 09:56:24 -03'00'

FLÁVIO JOSÉ ALVES
PREFEITO MUNICIPAL DE AVELINO LOPES – PI

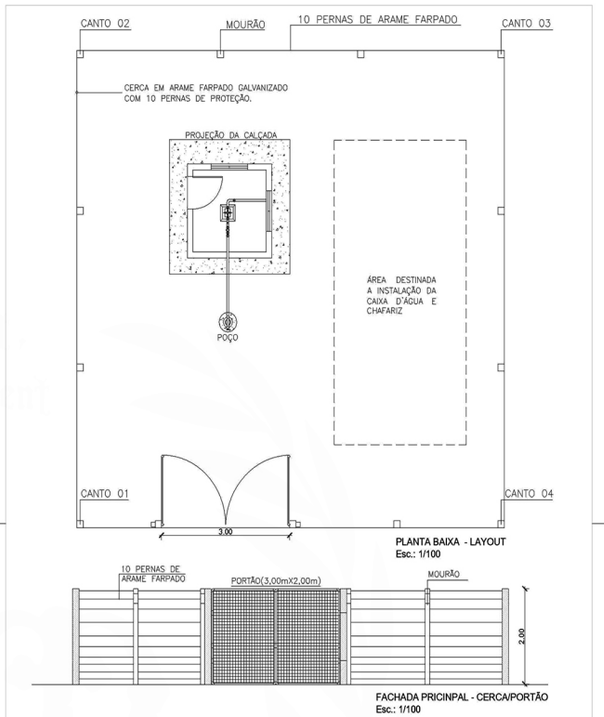

POÇO 01 - POVOADO DIONIZINHO			
	COORDENADAS UTM "E"	COORDENADAS UTM "S"	ZONA
POÇO	610752,40	8861177,92	23L
CANTO 01	610748,40	8861182,92	23L
CANTO 02	610758,40	8861182,92	23L
CANTO 03	610758,40	8861172,92	23L
CANTO 04	610748,40	8861172,92	23L

José Francisco da Silva Ribeiro
Engenheiro civil
CREA/PI nº: 1919571833

HSB
CONSULTORIA AMBIENTAL AGRICOLA

Assunto: PROJETO DE POÇOS TUBULARES			
Razão Social / CNPJ: PREFEITURA MUNICIPAL DE AVELINO LOPES – PIAUÍ			
Endereço: POVOADO DIONIZINHO/ZONA RURAL – AVELINO LOPES – PI			
Engenheiro Responsável / Crea: José Francisco da Silva Ribeiro–1919571833		Area total: 100,00m²	Area construída: 30,00m²
Desenho: José Francisco da Silva Ribeiro		Contatos: E–mail: eng.jfrancisco@outlook.com Eng. José Francisco (86)99424–2387 E–mail: darlanlb@hotmail.com Darlan Braga (86)99948–5759	
Escala: Indicada	Prancha: PJT - 01		
Data: DEZEMBRO /2025			

MEMORIAL DESCRITIVO DE LOCALIZAÇÃO DOS POÇOS TUBULARES E CERCAMENTO

Assunto: DESCRIÇÃO SITUAÇÃO FINAL – LOCAÇÃO
Imóvel: Lote de Terra rural
Endereço: Povoado Dionizinho
Município: Arraial - U.F: PI – BR

DA AREA DESMEMBRADA:

Área Total Inicial: 100,00 m²
Perímetro da área: 40,00m

LIMITES E CONFRONTAÇÕES

De frente para a Estrada vicinal, a poligonal inicia no ponto **P01**, de coordenadas UTM **E= 610748,40m** e **S= 8861182,92m** referidas ao MC 45° WGr. Sistema Geocêntrico SIRGAS 2000; deste segue com azimute de 0°00'00" e distância de 10,00m, até atingir o ponto **P02**, de coordenadas **E= 610758,40m** e **S= 8861182,92m**; deste segue com azimute de 90°00'00" e distância de 10,00m, até atingir o ponto **P03**, de coordenadas **E= 610758,40m** e **S= 8861172,92m**; deste segue com azimute de 180°00'00" e distância de 10,00m, até atingir o ponto **P04**, de coordenadas **E= 610758,40m** e **S= 8861172,92m**; deste segue com azimute de 270°00'00" até atingir o ponto **P01**, de coordenadas **E= 610748,40m** e **S= 8861172,92m**, e distância de 10,00m, confrontando com a Estrada vicinal, onde teve início a descrição deste perímetro.

José Francisco da Silva Ribeiro
Engenheiro civil
CREA/PI nº: 1919571833

(Continua na próxima página)

DIÁRIO OFICIAL DOS MUNICÍPIOS
"Verba Volant, Scripta Manent"

PREFEITURA MUNICIPAL DE
AVELINO LOPES
COMPROMISSO COM O POVO!

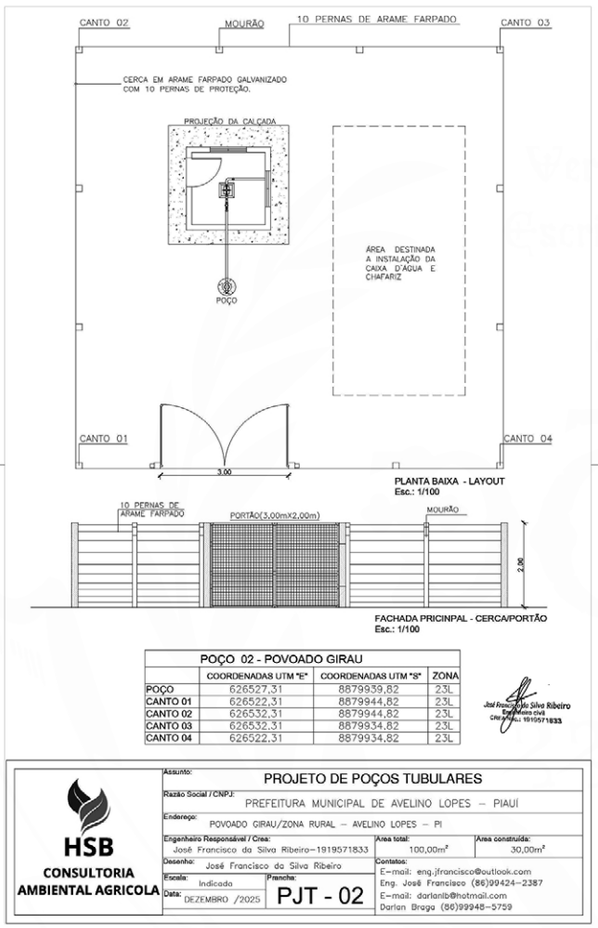

POÇO 02 - POVOADO GIRAU			
	COORDENADAS UTM "E"	COORDENADAS UTM "S"	ZONA
POÇO	626527,31	8879939,82	23L
CANTO 01	626522,31	8879944,82	23L
CANTO 02	626532,31	8879944,82	23L
CANTO 03	626532,31	8879934,82	23L
CANTO 04	626522,31	8879934,82	23L

José Francisco da Silva Ribeiro
Engenheiro civil
CREA/PI: 1919571833

HSB
CONSULTORIA AMBIENTAL AGRICOLA

Assunto: PROJETO DE POÇOS TUBULARES
Razão Social / CNPJ: PREFEITURA MUNICIPAL DE AVELINO LOPES – PIAUÍ
Endereço: POVOADO GIRAU/ZONA RURAL – AVELINO LOPES – PI
Engenheiro Responsável / Crea: José Francisco da Silva Ribeiro–1919571833
Area total: 100,00m²
Area construída: 30,00m²
Desenho: José Francisco da Silva Ribeiro
Escala: Indicada
Prancha: PJT - 02
Data: DEZEMBRO /2025
Contatos: E–mail: eng.jfrancisco@outlook.com
Eng. José Francisco (86)99424–2387
E–mail: darlanlb@hotmail.com
Darlan Braga (86)99948–5759

MEMORIAL DESCRITIVO DE LOCALIZAÇÃO DOS POÇOS TUBULARES E CERCAMENTO

Assunto: DESCRIÇÃO SITUAÇÃO FINAL – LOCAÇÃO
Imóvel: Lote de Terra rural
Endereço: Povoado Girau
Município: Arraial - U.F: PI – BR

DA AREA DESMEMBRADA:

Área Total Inicial: 100,00 m²
Perímetro da área: 40,00m

LIMITES E CONFRONTAÇÕES

De frente para a Estrada vicinal, a poligonal inicia no ponto **P01**, de coordenadas UTM **E= 626522,31m** e **S= 8879944,82m** referidas ao MC 45° WGr. Sistema Geocêntrico SIRGAS 2000; deste segue com azimute de 0°00'00" e distância de 10,00m, até atingir o ponto **P02**, de coordenadas **E= 626532,31m** e **S= 8879944,82m**; deste segue com azimute de 90°00'00" e distância de 10,00m, até atingir o ponto **P03**, de coordenadas **E= 626532,31m** e **S= 8879934,82m**; deste segue com azimute de 180°00'00" e distância de 10,00m, até atingir o ponto **P04**, de coordenadas **E= 626522,31m** e **S= 8879934,82m**; deste segue com azimute de 270°00'00" até atingir o ponto **P01**, de coordenadas **E= 626522,31m** e **S= 8879944,82m**, e distância de 10,00m, confrontando com a Estrada vicinal, onde teve início a descrição deste perímetro.

José Francisco da Silva Ribeiro
Engenheiro civil
CREA/PI: 1919571833

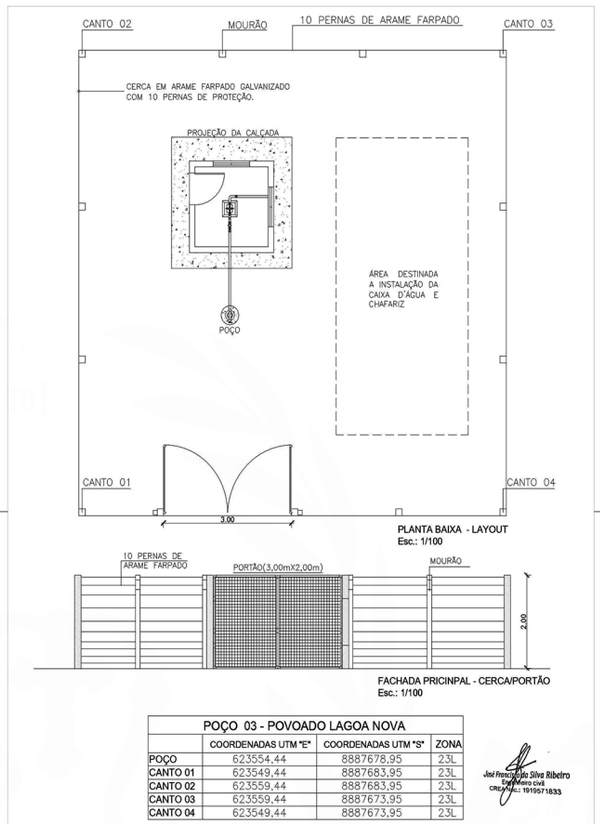

POÇO 03 - POVOADO LAGOA NOVA			
	COORDENADAS UTM "E"	COORDENADAS UTM "S"	ZONA
POÇO	623554,44	8887678,95	23L
CANTO 01	623549,44	8887683,95	23L
CANTO 02	623559,44	8887683,95	23L
CANTO 03	623559,44	8887673,95	23L
CANTO 04	623549,44	8887673,95	23L

José Francisco da Silva Ribeiro
Engenheiro civil
CREA/PI: 1919571833

HSB
CONSULTORIA AMBIENTAL AGRICOLA

Assunto: PROJETO DE POÇOS TUBULARES
Razão Social / CNPJ: PREFEITURA MUNICIPAL DE AVELINO LOPES – PIAUÍ
Endereço: POVOADO LAGOA NOVA/ZONA RURAL – AVELINO LOPES – PI
Engenheiro Responsável / Crea: José Francisco da Silva Ribeiro–1919571833
Area total: 100,00m²
Area construída: 30,00m²
Desenho: José Francisco da Silva Ribeiro
Escala: Indicada
Prancha: PJT - 03
Data: DEZEMBRO /2025
Contatos: E–mail: eng.jfrancisco@outlook.com
Eng. José Francisco (86)99424–2387
E–mail: darlanlb@hotmail.com
Darlan Braga (86)99948–5759

MEMORIAL DESCRITIVO DE LOCALIZAÇÃO DOS POÇOS TUBULARES E CERCAMENTO

Assunto: DESCRIÇÃO SITUAÇÃO FINAL – LOCAÇÃO
Imóvel: Lote de Terra rural
Endereço: Povoado Lagoa Nova
Município: Arraial - U.F: PI – BR

DA AREA DESMEMBRADA:

Área Total Inicial: 100,00 m²
Perímetro da área: 40,00m

LIMITES E CONFRONTAÇÕES

De frente para a Estrada vicinal, a poligonal inicia no ponto **P01**, de coordenadas UTM **E= 623549,44m** e **S= 8887683,95m** referidas ao MC 45° WGr. Sistema Geocêntrico SIRGAS 2000; deste segue com azimute de 0°00'00" e distância de 10,00m, até atingir o ponto **P02**, de coordenadas **E= 623559,44m** e **S= 8887683,95m**; deste segue com azimute de 90°00'00" e distância de 10,00m, até atingir o ponto **P03**, de coordenadas **E= 623559,44m** e **S= 8887683,95m**; deste segue com azimute de 180°00'00" e distância de 10,00m, até atingir o ponto **P04**, de coordenadas **E= 623559,44m** e **S= 8887673,95m**; deste segue com azimute de 270°00'00" até atingir o ponto **P01**, de coordenadas **E= 623549,44m** e **S= 8887683,95m**, e distância de 10,00m, confrontando com a Estrada vicinal, onde teve início a descrição deste perímetro.

José Francisco da Silva Ribeiro
Engenheiro civil
CREA/PI: 1919571833

(Continua na próxima página)

PREFEITURA MUNICIPAL DE
AVELINO LOPES
COMPROMISSO COM O POVO!

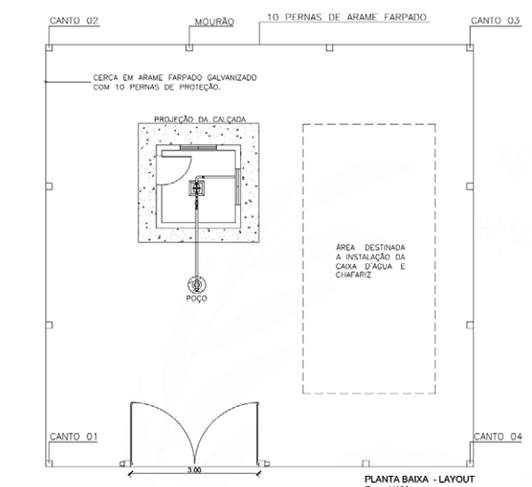

PLANTA BAIXA - LAYOUT
Esc.: 1/100

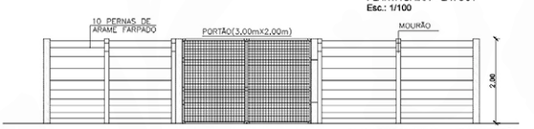

FACHADA PRICINPAL - CERCA/PORTÃO
Esc.: 1/100

POÇO 04 - POVOADO LAGOINHA			
	COORDENADAS UTM "E"	COORDENADAS UTM "S"	ZONA
POÇO	611397,83	8880388,97	23L
CANTO 01	611392,83	8880393,97	23L
CANTO 02	611402,83	8880393,97	23L
CANTO 03	611402,83	8880383,97	23L
CANTO 04	611392,83	8880383,97	23L

José Francisco da Silva Ribeiro
Engenheiro civil
CREA/PI.: 1919571833

HSB
CONSULTORIA AMBIENTAL AGRICOLA

Assunto: PROJETO DE POÇOS TUBULARES
Razão Social / CNPJ: PREFEITURA MUNICIPAL DE AVELINO LOPES – PIAUÍ
Endereço: POVOADO LAGOINHA/ZONA RURAL – AVELINO LOPES – PI
Engenheiro Responsável / Crea: José Francisco da Silva Ribeiro–1919571833
Area total: 100,00m² | Area construida: 30,00m²
Desenho: José Francisco da Silva Ribeiro
Escala: Indicado | Prancha: PJT - 04
Data: DEZEMBRO /2025
Contatos: E–mail: eng.jfrancisco@outlook.com
Eng. José Francisco (86)99424–2387
E–mail: darlanlb@hotmail.com
Darlan Braga (86)99948–5759

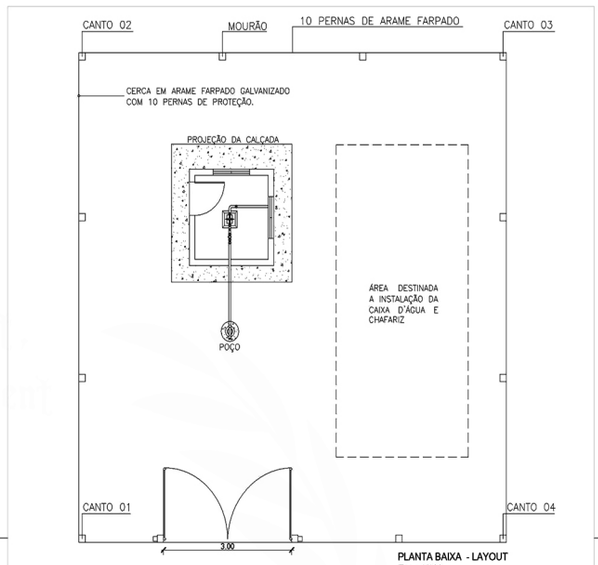

PLANTA BAIXA - LAYOUT
Esc.: 1/100

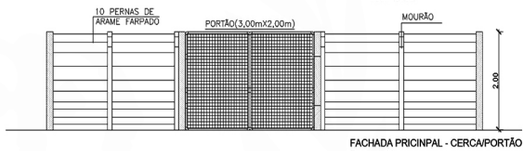

FACHADA PRICINPAL - CERCA/PORTÃO
Esc.: 1/100

POÇO 05 - POVOADO PALESTINA			
	COORDENADAS UTM "E"	COORDENADAS UTM "S"	ZONA
POÇO	601769,47	8887558,95	23L
CANTO 01	601764,47	8887563,95	23L
CANTO 02	601774,47	8887563,95	23L
CANTO 03	601774,47	8887553,95	23L
CANTO 04	601764,47	8887553,95	23L

José Francisco da Silva Ribeiro
Engenheiro civil
CREA/PI.: 1919571833

HSB
CONSULTORIA AMBIENTAL AGRICOLA

Assunto: PROJETO DE POÇOS TUBULARES
Razão Social / CNPJ: PREFEITURA MUNICIPAL DE AVELINO LOPES – PIAUÍ
Endereço: POVOADO PALESTINA/ZONA RURAL – AVELINO LOPES – PI
Engenheiro Responsável / Crea: José Francisco da Silva Ribeiro–1919571833
Area total: 100,00m² | Area construida: 30,00m²
Desenho: José Francisco da Silva Ribeiro
Escala: Indicado | Prancha: PJT - 05
Data: DEZEMBRO /2025
Contatos: E–mail: eng.jfrancisco@outlook.com
Eng. José Francisco (86)99424–2387
E–mail: darlanlb@hotmail.com
Darlan Braga (86)99948–5759

MEMORIAL DESCRITIVO DE LOCALIZAÇÃO DOS POÇOS TUBULARES E CERCAMENTO

Assunto: DESCRIÇÃO SITUAÇÃO FINAL – LOCAÇÃO
Imóvel: Lote de Terra rural
Endereço: Povoado Lagoinha
Município: Arraial - U.F: PI – BR

DA AREA DESMEMBRADA:

Área Total Inicial: 100,00 m²
Perímetro da área: 40,00m

LIMITES E CONFRONTAÇÕES

De frente para a Estrada vicinal, a poligonal inicia no ponto **P01**, de coordenadas UTM **E= 611392,83m** e **S= 8880393,97m** referidas ao MC 45° WGr. Sistema Geocêntrico SIRGAS 2000; deste segue com azimute de 0°00'00" e distância de 10,00m, até atingir o ponto **P02**, de coordenadas **E= 611402,83m** e **S= 8880393,97m**; deste segue com azimute de 90°00'00" e distância de 10,00m, até atingir o ponto **P03**, de coordenadas **E= 611402,83m** e **S= 8880383,97m**; deste segue com azimute de 180°00'00" e distância de 10,00m, até atingir o ponto **P04**, de coordenadas **E= 611392,83m** e **S= 8880383,97m**; deste segue com azimute de 270°00'00" até atingir o ponto **P01**, de coordenadas **E= 611392,83m** e **S= 8880393,97m**, e distância de 10,00m, confrontando com a Estrada vicinal, onde teve início a descrição deste perímetro.

José Francisco da Silva Ribeiro
Engenheiro civil
CREA/PI.: 1919571833

MEMORIAL DESCRITIVO DE LOCALIZAÇÃO DOS POÇOS TUBULARES E CERCAMENTO

Assunto: DESCRIÇÃO SITUAÇÃO FINAL – LOCAÇÃO
Imóvel: Lote de Terra rural
Endereço: Povoado Palestina
Município: Arraial - U.F: PI – BR

DA AREA DESMEMBRADA:

Área Total Inicial: 100,00 m²
Perímetro da área: 40,00m

LIMITES E CONFRONTAÇÕES

De frente para a Estrada vicinal, a poligonal inicia no ponto **P01**, de coordenadas UTM **E= 601764,47m** e **S= 8887563,95m** referidas ao MC 45° WGr. Sistema Geocêntrico SIRGAS 2000; deste segue com azimute de 0°00'00" e distância de 10,00m, até atingir o ponto **P02**, de coordenadas **E= 601774,47m** e **S= 8887563,95m**; deste segue com azimute de 90°00'00" e distância de 10,00m, até atingir o ponto **P03**, de coordenadas **E= 601774,47m** e **S= 8887553,95m**; deste segue com azimute de 180°00'00" e distância de 10,00m, até atingir o ponto **P04**, de coordenadas **E= 6017764,47m** e **S= 8887553,95m**; deste segue com azimute de 270°00'00" até atingir o ponto **P01**, de coordenadas **E= 601764,47m** e **S= 8887563,95m**, e distância de 10,00m, confrontando com a Estrada vicinal, onde teve início a descrição deste perímetro.

José Francisco da Silva Ribeiro
Engenheiro civil
CREA/PI.: 1919571833

(Continua na próxima página)

DIÁRIO OFICIAL DOS MUNICÍPIOS
"Verba Volant, Scripta Manent"

PREFEITURA MUNICIPAL DE
AVELINO LOPES
COMPROMISSO COM O POVO!

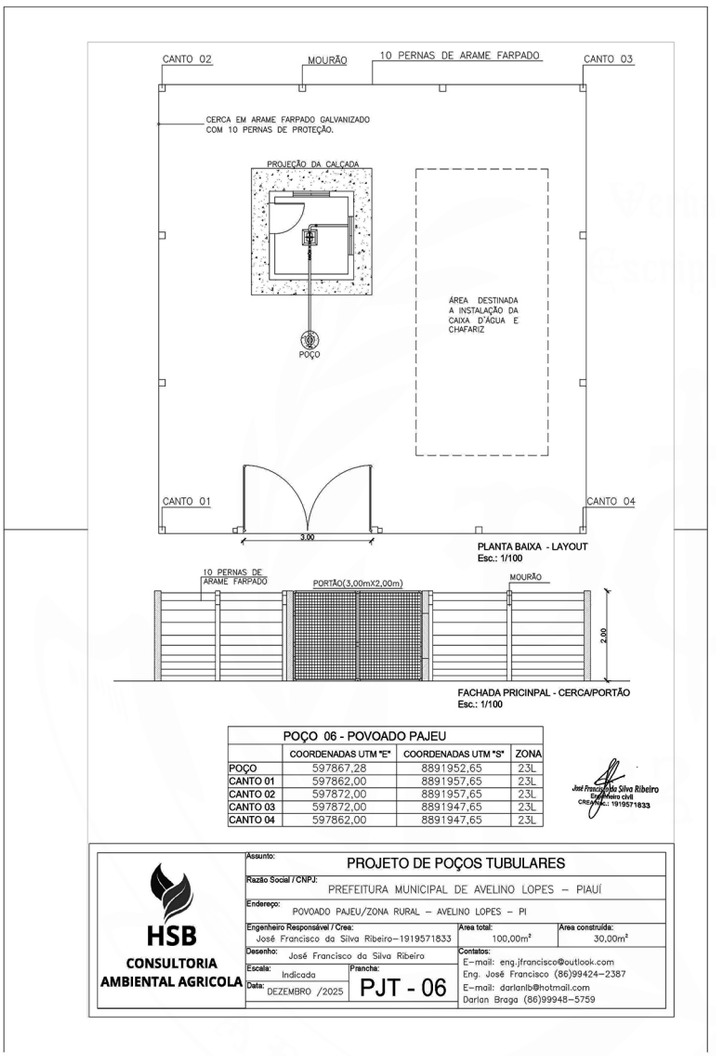

POÇO 06 - POVOADO PAJEU			
	COORDENADAS UTM "E"	COORDENADAS UTM "S"	ZONA
POÇO	597867,28	8891952,65	23L
CANTO 01	597862,00	8891957,65	23L
CANTO 02	597872,00	8891957,65	23L
CANTO 03	597872,00	8891947,65	23L
CANTO 04	597862,00	8891947,65	23L

José Francisco da Silva Ribeiro
Engenheiro civil
CREA/PI nº. 1919571833

HSB CONSULTORIA AMBIENTAL AGRICOLA	Assunto: PROJETO DE POÇOS TUBULARES		
	Razão Social / CNPJ: PREFEITURA MUNICIPAL DE AVELINO LOPES – PIAUÍ		
	Endereço: POVOADO PAJEU/ZONA RURAL – AVELINO LOPES – PI		
	Engenheiro Responsável / Crea: José Francisco da Silva Ribeiro–1919571833	Area total: 100,00m²	Area construída: 30,00m²
	Desenho: José Francisco da Silva Ribeiro	Contatos: E–mail: eng.jfrancisco@outlook.com Eng. José Francisco (86)99424–2387 E–mail: darlanlb@hotmail.com Darlan Braga (86)99948–5759	
	Escala: Indicada	Prancha: PJT - 06	
	Data: DEZEMBRO /2025		

MEMORIAL DESCRITIVO DE LOCALIZAÇÃO DOS POÇOS TUBULARES E CERCAMENTO

Assunto: DESCRIÇÃO SITUAÇÃO FINAL – LOCAÇÃO
Imóvel: Lote de Terra rural
Endereço: Povoado Pajeú
Município: Arraial - U.F: PI – BR

DA AREA DESMEMBRADA:

Área Total Inicial: 100,00 m²
Perímetro da área: 40,00m

LIMITES E CONFRONTAÇÕES

De frente para a Estrada vicinal, a poligonal inicia no ponto **P01**, de coordenadas UTM **E= 597862,00m** e **S= 8891957,65m** referidas ao MC 45° WGr. Sistema Geocêntrico SIRGAS 2000; deste segue com azimute de 0°00'00" e distância de 10,00m, até atingir o ponto **P02**, de coordenadas **E= 597872,00m** e **S= 8891957,65m**; deste segue com azimute de 90°00'00" e distância de 10,00m, até atingir o ponto **P03**, de coordenadas **E= 597872,00m** e **S= 8891947,65m**; deste segue com azimute de 180°00'00" e distância de 10,00m, até atingir o ponto **P04**, de coordenadas **E= 597872,00m** e **S= 8891947,65m**; deste segue com azimute de 270°00'00" até atingir o ponto **P01**, de coordenadas **E= 597862,00m** e **S= 8891947,65m**, e distância de 10,00m, confrontando com a Estrada vicinal, onde teve início a descrição deste perímetro.

José Francisco da Silva Ribeiro
Engenheiro civil
CREA/PI nº. 1919571833

Id:0CC5649A20AD97D6

GOVERNO MUNICIPAL DE BAIXA GRANDE DO RIBEIRO
Cuidar e Fazer é o nosso mandato
GESTÃO 2025-2028

EXTRATO DE CONTRATO

FUNDAMENTO LEGAL:
NORMA GERAL DA LEI FEDERAL DE LICITAÇÕES 14.133/2021, LEI COMPLEMENTAR 123/2006
PROCESSO ADMINISTRATIVO N°. **303/2025**
PROCEDIMENTO N°. **079/2025**
CONTRATO ADMINISTRATIVO Nº. **417/2025**
MODALIDADE: PREGÃO ELETRÔNICO

CONTRATANTE:
SECRETARIA MUNICIPAL DE SAÚDE DE BAIXA GRANDE DO RIBEIRO-PI CNPJ N°. 02.799.218/0001-83
ENDEREÇO: AVENIDA SEBASTIÃO LEAL, Nº 4140, CENTRO, BAIXA GRANDE DO RIBEIRO-PI

CONTRATADA:
AMB DISTRIBUIDORA DE MEDICAMENTO E MATERIAIS HOSPITALARES LTDA CNPJ Nº 37.885.137/0001-80
ENDEREÇO: AV BRASIL, Nº 1351, BAIRRO: VILA SALOME, CAMBE- PR, CEP: 86.192-000

GESTOR DO CONTRATO:
ÉRIKA LAURENE SOARES DA SILVA, PORTADORA DO CPF Nº 074.299.253-59

FISCAL DO CONTRATO:
RONALDO PEREIRA PAESLANDIM, PORTADOR DO CPF Nº 956.983.103-00

OBJETO:
CONTRATAÇÃO DE EMPRESA PARA FORNECIMENTO DE MATERIAIS PERMANENTES, EQUIPAMENTOS HOSPITALARES, MOBILIÁRIO ADMINISTRATIVO, EQUIPAMENTOS ODONTOLÓGICOS E DEMAIS ITENS CORRELATOS, DESTINADOS AO ATENDIMENTO DAS DEMANDAS DAS UNIDADES VINCULADAS À SECRETARIA MUNICIPAL DE SAÚDE DE BAIXA GRANDE DO RIBEIRO-PI, CONFORME ESPECIFICAÇÕES, QUANTIDADES E CONDIÇÕES DETALHADAS NO TERMO DE REFERÊNCIA

FONTE DE RECURSOS:
ICMS – FPM – FMS/FUS – PAB – COFINANCIAMENTO – ATENÇÃO BÁSICA – VIGILÂNCIA EM SAÚDE – RECURSOS FEDERAIS - E OUTROS RECURSOS PRÓPRIOS DO MUNICÍPIO

VALOR TOTAL PARA OS ITENS: 26, 52:
R$ 49.220,00 (QUARENTA E NOVE MIL DUZENTOS E VINTE REAIS)

III – DA FORMA DE PAGAMENTO:
PAGOS DE ACORDO COM OS PRODUTOS FORNECIDOS.

IV – DO PRAZO:
O PRAZO DE VIGÊNCIA DO CONTRATO SERÁ DE 12 (DOZE) MESES A PARTIR DA DATA DA SUA ASSINATURA E A CORRESPONDENTE PUBLICAÇÃO

DATA DA HOMOLOGAÇÃO:
22 DE DEZEMBRO DE 2025

DATA DA ADJUDICAÇÃO:
18 DE DEZEMBRO DE 2025

DATA DA ASSINATURA:
22 DE DEZEMBRO DE 2025

SIGNATÁRIOS:
SECRETARIA MUNICIPAL DE SAÚDE DE BAIXA GRANDE DO RIBEIRO-PI CNPJ N°. 02.799.218/0001-83 (CONTRATANTE)
AMB DISTRIBUIDORA DE MEDICAMENTO E MATERIAIS HOSPITALARES LTDA CNPJ Nº 37.885.137/0001-80 (CONTRATADO)

CNPJ: 41.522.178/0001-80
Praça Chulquinho Ezequiel 2222, Centro
CEP:64868-000 - Baixa Grande do Ribeiro Piauí
Fone: (89)3570-1473 EMAIL: prefeituradebaixagrande@bol.com.br

Id:0E28AA127E3797DD

GOVERNO MUNICIPAL DE BAIXA GRANDE DO RIBEIRO
Cuidar e Fazer é o nosso mandato
GESTÃO 2025-2028

EXTRATO DE CONTRATO

FUNDAMENTO LEGAL:
NORMA GERAL DA LEI FEDERAL DE LICITAÇÕES 14.133/2021, LEI COMPLEMENTAR 123/2006
PROCESSO ADMINISTRATIVO N°. **303/2025**
PROCEDIMENTO N°. **079/2025**
CONTRATO ADMINISTRATIVO Nº. **418/2025**
MODALIDADE: PREGÃO ELETRÔNICO

CONTRATANTE:
SECRETARIA MUNICIPAL DE SAÚDE DE BAIXA GRANDE DO RIBEIRO-PI CNPJ N°. 02.799.218/0001-83
ENDEREÇO: AVENIDA SEBASTIÃO LEAL, Nº 4140, CENTRO, BAIXA GRANDE DO RIBEIRO-PI

CONTRATADA:
EVENI DA SILVA BRITO (VENY CONFECCOES) CNPJ Nº 08.086.600/0001-26
ENDEREÇO: R SAO FRANCISCO, Nº 512, CENTRO, PICOS- PI, CEP: 64.600-012

GESTOR DO CONTRATO:
ÉRIKA LAURENE SOARES DA SILVA, PORTADORA DO CPF Nº 074.299.253-59

FISCAL DO CONTRATO:
RONALDO PEREIRA PAESLANDIM, PORTADOR DO CPF Nº 956.983.103-00

OBJETO:
CONTRATAÇÃO DE EMPRESA PARA FORNECIMENTO DE MATERIAIS PERMANENTES, EQUIPAMENTOS HOSPITALARES, MOBILIÁRIO ADMINISTRATIVO, EQUIPAMENTOS ODONTOLÓGICOS E DEMAIS ITENS CORRELATOS, DESTINADOS AO ATENDIMENTO DAS DEMANDAS DAS UNIDADES VINCULADAS À SECRETARIA MUNICIPAL DE SAÚDE DE BAIXA GRANDE DO RIBEIRO-PI, CONFORME ESPECIFICAÇÕES, QUANTIDADES E CONDIÇÕES DETALHADAS NO TERMO DE REFERÊNCIA

FONTE DE RECURSOS:
ICMS – FPM – FMS/FUS – PAB – COFINANCIAMENTO – ATENÇÃO BÁSICA – VIGILÂNCIA EM SAÚDE – RECURSOS FEDERAIS - E OUTROS RECURSOS PRÓPRIOS DO MUNICÍPIO

VALOR TOTAL PARA OS ITENS: 14, 23, 47, 50, 51:
R$ 55.540,15 (CINQUENTA E CINCO MIL QUINHENTOS E QUARENTA REAIS E QUINZE CENTAVOS)

III – DA FORMA DE PAGAMENTO:
PAGOS DE ACORDO COM OS PRODUTOS FORNECIDOS.

IV – DO PRAZO:
O PRAZO DE VIGÊNCIA DO CONTRATO SERÁ DE 12 (DOZE) MESES A PARTIR DA DATA DA SUA ASSINATURA E A CORRESPONDENTE PUBLICAÇÃO

DATA DA HOMOLOGAÇÃO:
22 DE DEZEMBRO DE 2025

DATA DA ADJUDICAÇÃO:
18 DE DEZEMBRO DE 2025

DATA DA ASSINATURA:
22 DE DEZEMBRO DE 2025

SIGNATÁRIOS:
SECRETARIA MUNICIPAL DE SAÚDE DE BAIXA GRANDE DO RIBEIRO-PI CNPJ N°. 02.799.218/0001-83 (CONTRATANTE)
EVENI DA SILVA BRITO (VENY CONFECCOES) CNPJ Nº 08.086.600/0001-26 (CONTRATADO)

CNPJ: 41.522.178/0001-80
Praça Chulquinho Ezequiel 2222, Centro
CEP:64868-000 - Baixa Grande do Ribeiro Piauí
Fone: (89)3570-1473 EMAIL: prefeituradebaixagrande@bol.com.br